APRESENTAÇÃO DE CAPTAÇÃO SEED — 2026

Loteamento Jardins do Mar

O maior loteamento planejado do Litoral Norte de Maceió, no alto de Ipioca, com vista privilegiada para o Oceano Atlântico. Zona de Interesse Turístico (ZIT). Captação seed de R$ 3.000.000 para início das etapas de regularização e infraestrutura.

186K	255	ZIT	+18%	R$3M
M² ÁREA TOTAL	LOTES RESIDENCIAIS	ZONEAMENTO	VALORIZ. MACEIÓ '23	CAPTAÇÃO SEED

SUMÁRIO EXECUTIVO

Visão Geral *do Empreendimento*

Este relatório apresenta uma análise estratégica completa do Loteamento Jardins do Mar, empreendimento de loteamento residencial planejado localizado no alto de Ipioca, Litoral Norte de Maceió, Alagoas. O documento consolida dados técnicos do terreno, análise de mercado imobiliário, estrutura financeira da captação seed e recomendações estratégicas para o investidor.

O empreendimento ocupa uma área de 186.268,23 m² em Zona de Interesse Turístico (ZIT), com aprovação de anteprojeto urbanístico para 255 lotes residenciais. A incorporadora é T.M. da Silva Godoy Incorporação Imobiliária SPE LTDA, empresa de propósito específico constituída para o desenvolvimento deste projeto.

A captação seed de R$ 3.000.000 tem como objetivo financiar as etapas de regularização fundiária, aprovação dos projetos junto aos órgãos competentes e início da infraestrutura primária — viabilizando o lançamento comercial dos lotes em horizonte de 15 a 18 meses.

DADOS DO EMPREENDIMENTO

EMPREENDIMENTO	**Loteamento Jardins do Mar**
INCORPORADORA	**T.M. da Silva Godoy SPE LTDA**
CNPJ	**63.419.446/0001-75**
LOCALIZAÇÃO	**Ipioca, Maceió — AL**
ZONEAMENTO	**ZIT — Zona de Interesse Turístico**
ÁREA TOTAL	**186.268,23 m²**
LOTES RESIDENCIAIS	**255 unidades**
CAPTAÇÃO SEED	**R$ 3.000.000**

INDICADORES-CHAVE

DESTINAÇÃO — LOTES	**45,45% da área**
ÁREA PERMEÁVEL	**23,78%**
SISTEMA VIÁRIO	**20,40%**
ROI PROJETADO	**3× a 5×**
HORIZONTE	**36–48 meses**
VALORIZ. MACEIÓ 2023	**+18,0% a.a.**
VALORIZ. MACEIÓ 2024	**+10,5% a.a.**
PREÇO/M² MACEIÓ	**R$ 9.307 (FipeZAP)**

Um ativo raro *no momento certo.*

O Jardins do Mar está posicionado em um dos últimos grandes terrenos urbanos do Litoral Norte de Maceió — a área de maior crescimento imobiliário do Nordeste. Com 186.268 m² em Zona ZIT, o projeto combina escassez de ativo, localização privilegiada e vento favorável de infraestrutura.

A duplicação da AL-101 Norte, em processo, reduzirá o tempo de deslocamento para Maceió e impulsionará o adensamento nos próximos 36 meses — janela exata do lançamento comercial planejado. Este catalisador externo, aliado à escassez de terrenos similares na região, cria uma janela de oportunidade rara para o investidor qualificado.

Maceió registrou **+18% em 2023** e **+10,5% em 2024**, ambos acima da média nacional. O metro quadrado da capital alagoana é hoje o mais valorizado do Nordeste segundo o índice FipeZAP, com R$ 9.307/m² em 2024.

OS QUATRO PILARES DA TESE

01 · Vista Mar Privilegiada

No alto de Ipioca, visibilidade direta para o Oceano Atlântico — diferencial premium que impacta diretamente a precificação dos lotes e garante demanda de comprador final qualificado.

02 · Catalisador AL-101 Norte

Duplicação da rodovia reduzirá em estimados 40% o tempo de deslocamento até o centro de Maceió, impulsionando demanda e valorização nos próximos 36 meses.

03 · Ativo Estruturado e Documentado

186.268 m² em Zona ZIT com anteprojeto urbanístico aprovado, levantamento topográfico TecnoGIS completo e SPE constituída. Documentação íntegra e auditável.

04 · ROI Projetado de 3× a 5×

Retorno sobre capital projetado entre 3× e 5× em horizonte de 24 a 48 meses, com garantia real sobre o ativo imobiliário e participação proporcional ao aporte.

VALORIZAÇÃO IMOBILIÁRIA — MACEIÓ VS. BRASIL

MERCADO	VALORIZ. 2023	VALORIZ. 2024
Maceió	+18,0%	+10,5%
Média Nordeste	+7,2%	+6,8%
Média Brasil	+5,8%	+5,2%
CDI (referência)	+13,1%	+10,9%
Poupança (referência)	+6,2%	+6,2%

PREÇO/M² — CAPITAIS DO NORDESTE (FIPEZAP)

CAPITAL	R$/M² (2024)	POSIÇÃO
Maceió	R$ 9.307	#1 Nordeste
Recife	R$ 8.940	#2
Fortaleza	R$ 7.820	#3
Salvador	R$ 7.450	#4
Natal	R$ 6.980	#5

CONTEXTO ESTRATÉGICO

Maceió ocupa a posição de capital nordestina com maior valorização imobiliária acumulada nos últimos dois anos, superando consistentemente a média nacional. O Litoral Norte — especialmente Ipioca — concentra a valorização mais expressiva, impulsionada pela combinação de demanda turística, duplicação da AL-101 e escassez de terrenos ZIT disponíveis.

02 / O ATIVO

186 mil m² com vista *para o Atlântico.*

Sítio Rêgo, AL-101 Norte, Ipioca, Maceió-AL — Zona de Interesse Turístico (ZIT). Terreno em posição topográfica elevada com visibilidade direta para o Oceano Atlântico e acesso imediato pela principal rodovia do Litoral Norte de Alagoas.

ESPECIFICAÇÕES TÉCNICAS DO TERRENO

ÁREA TOTAL	**186.268,23 m²**
ZONEAMENTO MUNICIPAL	**ZIT — Zona Int. Turístico**
ENDEREÇO	**Sítio Rêgo, AL-101 Norte**
BAIRRO / LOCALIDADE	**Ipioca, Maceió — AL**
CEP	**57.039-000**
LEVANTAMENTO TOPOGRÁFICO	**TecnoGIS — concluído**
STATUS DOCUMENTAL	**Documentação completa**

DISTRIBUIÇÃO DE ÁREAS — ANTEPROJETO APROVADO

DESTINAÇÃO	PERCENTUAL	ÁREA (M²)
Lotes Residenciais	45,45%	84.669
Sistema Viário	20,40%	38.007
Áreas Verdes / Permeáveis	23,78%	44.299
Equipamentos Comunitários	7,37%	13.730
Institucional	3,00%	5.588
Total	100%	186.268

TIPOLOGIA DOS LOTES

DIMENSÃO	ÁREA	PERFIL	QUADRAS
12 × 30 m	360 m²	Padrão	B–T (maioria)
15 × 30 m	450 m²	Intermediário	Canto e destaque
20 × 30 m	600 m²	**Premium**	**K, L, M — Vista**

QUATRO ÁREAS DO PROJETO

ÁREA	PROGRAMA URBANÍSTICO
Área 01	Guarita, Mirante e Área de Lazer — Acesso principal
Área 02	Residencial com Lazer — Quadras K, L, M, N, O
Área 03	Residencial — Quadras P, Q, R, S, T
Implantação Geral	Vista completa do Loteamento Jardins do Mar

▸ *As plantas de implantação de cada área encontram-se nos **Anexos I a IV** ao final deste relatório.*

VANTAGEM LOCACIONAL

A posição topográfica elevada do terreno garante visibilidade permanente para o Oceano Atlântico em praticamente todos os lotes das Quadras K, L e M — fator de valorização premium de 20% a 35% sobre o preço de lotes similares sem vista mar no mesmo município.

R$ 3M de captação. *Potencial de R$ 60M+.*

Captação seed estruturada para financiar as etapas críticas de regularização, aprovação e infraestrutura primária do loteamento, viabilizando o lançamento comercial e destravando o potencial de receita estimado em R$ 60 milhões com a venda dos 255 lotes.

DESTINO DA CAPTAÇÃO — R$ 3.000.000

USO DOS RECURSOS	VALOR	%
Regularização fundiária	R$ 800.000	26,7%
Projetos e aprovações (SEFIC/ CREA)	R$ 600.000	20,0%
Infraestrutura — Fase 1 (redes/vias)	R$ 900.000	30,0%
Capital de giro e contingência	R$ 700.000	23,3%
Total Captação Seed	R$ 3.000.000	100%

ESTRUTURA DO INVESTIMENTO

NATUREZA	**Participação em SPE**
INSTRUMENTO	**Contrato de Investimento ou CCB**
RODADA	**Seed Round · 2026**
VAGAS	**Limitadas**
GARANTIA	**Garantia real sobre o ativo**
PARTICIPAÇÃO	**Proporcional ao aporte**
RELATÓRIOS	**Mensais de progresso**
GOVERNANÇA	**Assembleia trimestral de sócios**

CENÁRIOS DE RETORNO PROJETADOS

CENÁRIO	VELOCIDADE DE VENDAS	ROI	PRAZO
Conservador	Venda gradual — 40 meses	3×	48 meses
Base	Venda lotes — 24–36 meses	4×	36 meses
Otimista	Lançamento acelerado	5×	24–30 meses

RECEITA POTENCIAL BRUTA ESTIMADA

R$ 60M+

255 lotes × preço médio estimado de R$ 235.000/lote (considerando mix de tipologias padrão, intermediário e premium com vista mar). Projeção baseada em pesquisa de preços de loteamentos similares em Maceió e região. Não constitui garantia de receita.

CRONOGRAMA DE EXECUÇÃO

FASE	PRAZO	ENTREGA
Regularização e Aprovação	Meses 1–6	SEFIC, CREA, Prefeitura
Infraestrutura Fase 1	Meses 7–14	Redes, vias, demarcação
Lançamento Comercial	Mês 15+	Abertura de vendas ao público
Infraestrutura Fase 2	Meses 16–24	Pavimentação, acabamentos
Entrega das Chaves	Meses 36–48	Closing e registro dos lotes

Arquitetura que *escuta o território.*

O anteprojeto urbanístico do Loteamento Jardins do Mar foi desenvolvido com base em um conceito que valoriza a topografia natural, maximiza a vista mar e cria uma hierarquia de espaços que equilibra privacidade, convivência e sustentabilidade ambiental.

CONCEITO URBANÍSTICO

O nome *Jardins do Mar* reflete a paleta cromática que inspira o projeto: o azul profundo do Atlântico, o verde das matas de restinga, a argila e o vermelho queimado do solo alagoano, o branco das casas de veraneio nordestinas e o dourado da luz rasante do entardecer sobre o mar.

O traçado viário foi concebido para minimizar cortes de terra e respeitar as curvas de nível do terreno — estratégia que reduz custos de terraplenagem e preserva a topografia elevada que confere vista mar aos lotes das quadras premium.

INFRAESTRUTURA PREVISTA

- **Sistema viário:** Pavimentação asfáltica com calçadas e ciclovias
- **Rede de energia elétrica:** Distribuição subterrânea nas vias principais
- **Abastecimento de água:** Rede pública CASAL com reservatórios elevados
- **Esgotamento sanitário:** Rede coletora com estação de tratamento própria
- **Drenagem pluvial:** Sistema dimensionado para chuvas de 50 anos de recorrência
- **Iluminação pública:** LED de alta eficiência em todos os logradouros
- **Telecomunicações:** Dutos para fibra óptica e internet de alta velocidade

ÁREAS DE CONVIVÊNCIA E LAZER

- **Guarita e Portaria:** Controle de acesso com câmeras 24h
- **Mirante:** Área contemplativa com vista 360° para o Atlântico
- **Praças de convivência:** Distribuídas entre os setores residenciais
- **Equipamentos comunitários:** Salão de eventos e área de esportes
- **Trilhas ecológicas:** Integradas à vegetação nativa preservada

PARÂMETROS URBANÍSTICOS — ZIT IPIOCA

PARÂMETRO	VALOR / LIMITE
Lote mínimo	300 m²
Taxa de ocupação máx.	50%
Coeficiente aproveit. máx.	1,0
Altura máxima	2 pavimentos
Recuo frontal mínimo	4,0 m
Recuo lateral mínimo	1,5 m
Área permeável mínima	20%
Uso permitido	Residencial e hoteleiro

SUSTENTABILIDADE E MEIO AMBIENTE

- **Área de Preservação Permanente (APP):** Faixa de 30m preservada ao longo do curso d'água interno
- **Compensação ambiental:** Projeto de arborização com espécies nativas da restinga alagoana
- **Permeabilidade mínima:** 23,78% da área total destinada a solo permeável
- **Gestão de resíduos sólidos:** Pontos de coleta seletiva em todos os setores

LICENÇAS E APROVAÇÕES

ANTEPROJETO URBANÍSTICO	**Aprovado** (ver Anexos I–IV)
LEVANTAMENTO TOPOGRÁFICO	**Concluído (TecnoGIS)** (ver Anexo V)
LICENÇA AMBIENTAL	**Em processo — SEMA-AL**
APROVAÇÃO PREFEITURA	**Em processo — Maceió**
REGISTRO DE INCORPORAÇÃO	**Previsto após aprovações**

SWOT do *empreendimento.*

Avaliação das forças, fraquezas, oportunidades e ameaças do Loteamento Jardins do Mar no contexto do mercado imobiliário alagoano, com foco nos fatores determinantes para o sucesso da captação seed e do lançamento comercial.

FORÇAS

- Localização única no alto de Ipioca com vista direta para o Atlântico
- 186.268 m² em Zona ZIT — escassez de ativos similares na região
- AL-101 Norte como catalisador externo de valorização
- Anteprojeto urbanístico aprovado com conceito premium
- SPE constituída com estrutura jurídica robusta e CNPJ ativo
- 255 lotes com tipologias diversificadas — padrão ao premium com vista mar
- Levantamento topográfico TecnoGIS completo e auditável
- Documentação íntegra sem pendências judiciais ou fiscais

FRAQUEZAS

- Regularização ainda em andamento — risco de atraso nos licenciamentos
- Dependência da duplicação da AL-101 para plena realização do adensamento
- Necessidade da captação seed para início efetivo das obras
- Mercado de lotes de alto padrão em Ipioca com histórico limitado de transações
- Infraestrutura regional ainda em desenvolvimento (saneamento/energia)

OPORTUNIDADES

- Maceió com maior valorização imobiliária do Nordeste — +18% em 2023
- Demanda crescente por loteamentos planejados com infraestrutura completa
- Zona ZIT habilita uso residencial, hoteleiro e turístico — mix de demanda
- Marco legal dos loteamentos favorece securitização futura dos recebíveis
- Tendência de migração para municípios e regiões litorâneas pós-pandemia
- Acesso à AL-101 conecta o empreendimento ao aeroporto e centro em 20 min
- Duplicação prevista reduz barreira de distância percebida pelo comprador

AMEAÇAS

- Elevação da taxa Selic pode impactar o crédito imobiliário e a demanda
- Atraso em licenciamentos ambientais (SEMA-AL) pode comprometer prazos
- Concorrência de loteamentos já aprovados e em comercialização na região
- Volatilidade do cenário econômico nacional afetando o perfil do investidor
- Variação no custo de materiais de construção impactando orçamento de obras

VANTAGEM COMPETITIVA SUSTENTÁVEL

O principal diferencial competitivo do Jardins do Mar é estrutural e não replicável no curto prazo: a combinação de posição topográfica elevada com vista mar, localização em ZIT com possibilidade de uso hoteleiro e a escassez de terrenos com essas características no Litoral Norte de Maceió. Novos competidores não terão acesso a ativos similares disponíveis na região, criando uma vantagem de primeiro movimento com alto potencial de valorização.

06 / COMO PARTICIPAR

Próximos *passos.*

O processo de entrada no Seed Round do Loteamento Jardins do Mar é estruturado em três etapas para garantir segurança jurídica, transparência e alinhamento de expectativas entre os investidores e a SPE incorporadora.

ETAPA 01

Due Diligence

Acesso ao data room completo: documentação do terreno, matrícula e certidões, levantamento topográfico TecnoGIS, anteprojeto urbanístico aprovado, memorial descritivo e pareceres jurídicos. Prazo: 15 dias para análise.

ETAPA 02

Instrumento Jurídico

Formalização via contrato de participação em SPE ou Cédula de Crédito Bancário (CCB), conforme perfil e preferência do investidor. Participação proporcional ao aporte, com garantia real sobre o ativo imobiliário.

ETAPA 03

Aporte & Execução

Após closing, início imediato das etapas de regularização e aprovação. Relatórios mensais de progresso com fotos e marcos atingidos. Assembleia de sócios trimestral para prestação de contas.

TOP 5 AÇÕES IMEDIATAS APÓS A CAPTAÇÃO

#	AÇÃO	PRAZO	RESPONSÁVEL
01	**Protocolar pedido de licença ambiental** na SEMA-AL com documentação completa	Mês 1	Equipe Jurídica / SPE
02	**Submeter projeto à Prefeitura de Maceió** para aprovação do loteamento	Mês 1–2	Engenharia / SPE
03	**Contratar empresa de infraestrutura** para início dos serviços Fase 1	Mês 2–3	SPE / Gerência de Obras
04	**Desenvolver material de vendas** e campanha de pré-lançamento para captação de leads	Mês 4–6	Marketing / SPE
05	**Evento de lançamento comercial** para corretores e investidores qualificados	Mês 15	SPE / Incorporadora

INTERESSE EM PARTICIPAR

Para solicitar acesso ao data room completo, manifestar interesse de investimento ou obter informações adicionais sobre a estrutura da SPE e do instrumento jurídico de participação, entre em contato com a equipe de relações com investidores do Loteamento Jardins do Mar. **Vagas limitadas. Seed Round 2026.**

NOTA DE ENCERRAMENTO

Relatório elaborado em abril de 2026. Uso exclusivo da equipe de relações com investidores e de investidores qualificados que assinaram acordo de confidencialidade com a SPE incorporadora. Reprodução, distribuição ou divulgação não autorizadas são expressamente proibidas.

AVISO LEGAL: Este relatório foi elaborado com base em dados públicos disponíveis, levantamento topográfico TecnoGIS, anteprojeto urbanístico aprovado, dados do mercado imobiliário FipeZAP e projeções elaboradas pela equipe técnica da SPE. Projeções financeiras são estimativas baseadas em premissas de mercado e não constituem garantia de retorno. Recomenda-se revisão periódica desta estratégia conforme o cenário evolui.

Produzido por **Ronald Hancock** — Consultoria em Marketing Imobiliário e Estratégia de Captação · Abril de 2026

ANEXOS / PLANTAS DO PROJETO

Implantação e *Plantas das Áreas.*

Plantas do anteprojeto urbanístico do Loteamento Jardins do Mar — Condomínio Ipioca Mar Residence, elaboradas com base no levantamento topográfico TecnoGIS. Documentos disponíveis em escala original no data room do empreendimento.

ANEXO I

Planta de Implantação — Área 01

Guarita, Mirante e Área de Lazer · Acesso Principal

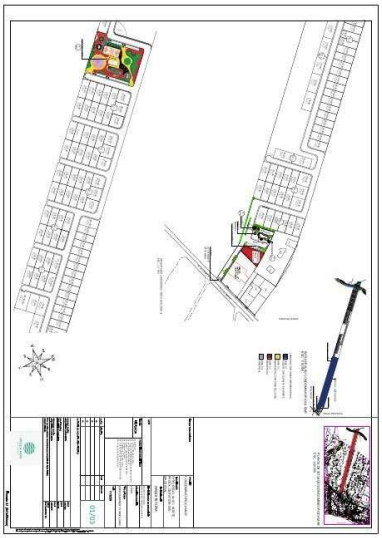

Área 01 — Guarita, Mirante e Lazer

Esc. 1/1.000 · Anteprojeto Urbanístico

ANEXO II

Planta de Implantação — Área 02

Residencial com Lazer · Quadras K, L, M, N, O

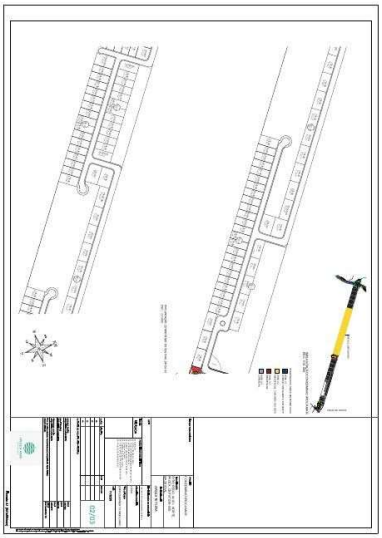

Área 02 — Residencial com Lazer

Esc. 1/1.000 · Quadras K, L, M, N, O

ANEXO III

Planta de Implantação — Área 03

Residencial · Quadras P, Q, R, S, T

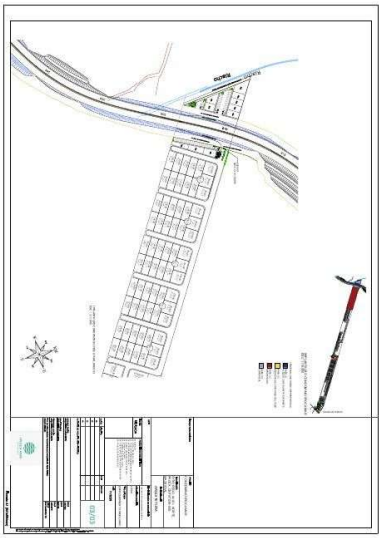
RUA
RUA
RUA

A N E X O V

Levantamento Topográfico Planialtimétrico — Vista Geral

Loteamento Residencial no Alto de Ipioca · ADF Arquitetura e Urbanismo · TecnoGIS · Folha 1001

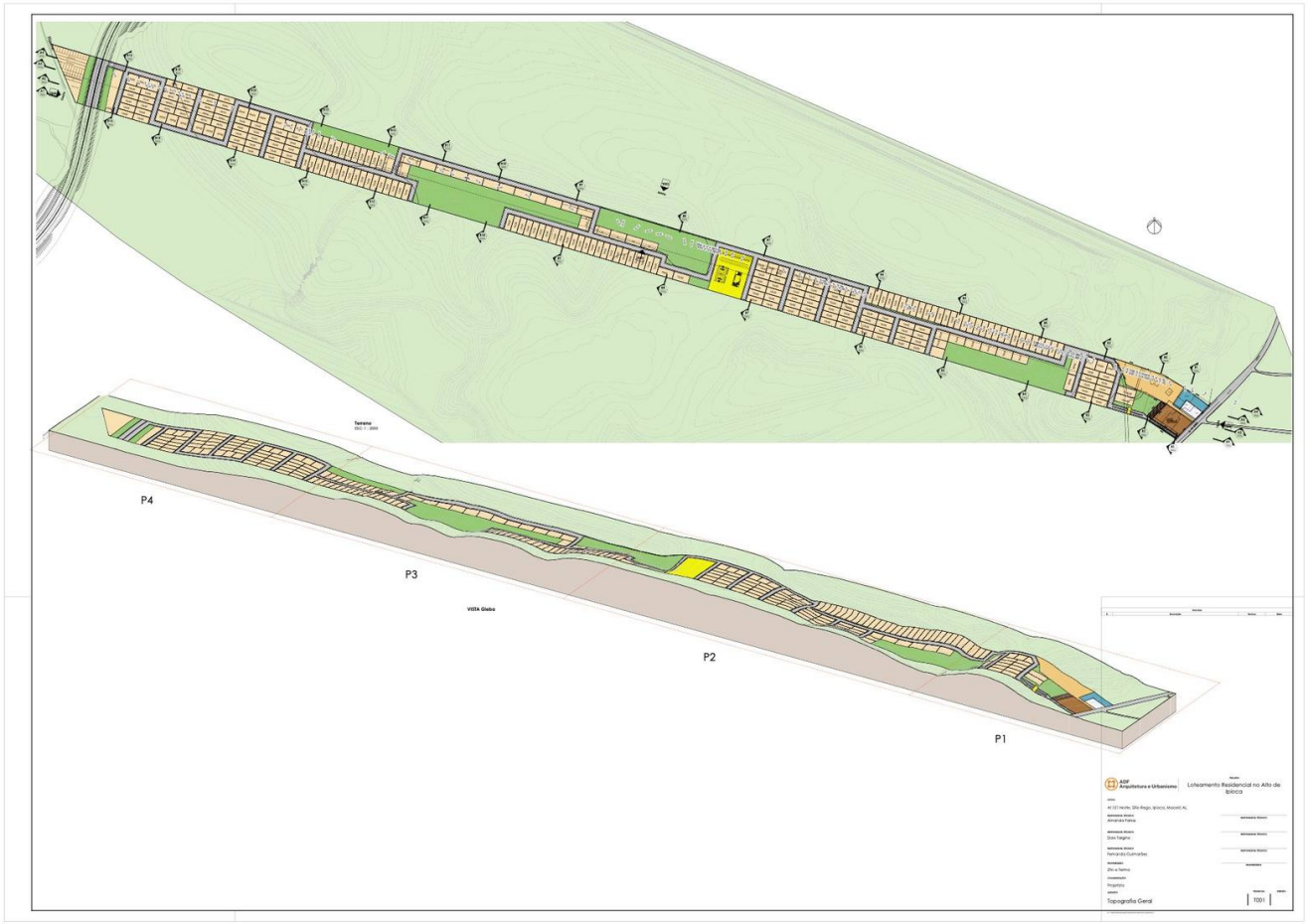

Topografia Geral — Implantação e perfis do terreno · AL-101 Norte, Sítio Rêgo, Ipioca, Maceió-AL

Esc. 1/2.000 · ADF Arquitetura e Urbanismo · Folha 1001